Dopravný podnik mesta Prešov, akciová spoločnosť
Bardejovská 7, 080 06 Ľubotice

Ročný projekt organizácie MHD v záujmovom území mesta Prešov na rok 2026

Prešov, november 2025

Ing. Juraj Hrehorčák
výkonný riaditeľ

Spracovali:
Ing. Radomír Ragan
riaditeľ dopravného úseku

Ing. Peter Koštialik
technický pracovník

1. ÚVOD

Tento ročný projekt organizácie MHD sa vzťahuje na organizáciu mestskej hromadnej dopravy v meste Prešove a v obciach Bzenov, Dulova Ves, Fintice, Haniska, Ľubotice, Malý Šariš, Podhradík, Ruská Nová Ves, Teriakovce, Vyšná Šebastová, Záborské a v meste Veľký Šariš (ďalej len „záujmové územie mesta Prešov“) na kalendárny rok 2026 (ďalej „RPO 2026“) a je spracovaný v zmysle Rámcovej zmluvy o službách vo verejnom záujme a zabezpečení mestskej hromadnej dopravy osôb v meste Prešov na roky 2017-2026 zo dňa 22. 12. 2016 v znení neskorších dodatkov uzatvorenej s mestom Prešov.

Organizácia autobusovej a trolejbusovej dopravy od 01. 01. 2026 je spracovaná v súlade s cestovnými poriadkami platnými od 01. 01. 2026 s požadovanou úpravou na kalendárny rok 2026.

V celkových kilometrových výkonoch na kalendárny rok 2026 sú započítané výkony na denných a nočných linkách MHD, školských spojoch a manipulačné jazdy vozidiel.

2. POUŽITÉ POJMY A SKRATY

Dopravca – Dopravný podnik mesta Prešov, akciová spoločnosť
MHD – mestská hromadná doprava
RPO – ročný projekt organizácie MHD
AU – autobusová trakcia
TR – trolejbusová trakcia
PD – pracovný deň so školským vyučovaním (pracovný deň školský)
PPD – pracovný deň bez školského vyučovania (pracovný deň prázdniny)
SO – sobota
NE – nedeľa
SV – sviatok

3. PREVÁDZKOVÉ REŽIMY

3.1 Základný prevádzkový režim - typy prevádzkových dní a časový režim prevádzky

1. Pracovný deň školský - všetky pracovné dni so školským vyučovaním
   a. Denná prevádzka: $5^{00} – 22^{30}$
   b. Nočná prevádzka $22^{30} – 5^{00}$
2. Pracovný deň prázdniny - všetky pracovné dni bez školského vyučovania
   a. Denná prevádzka: $5^{00} – 22^{30}$
   b. Nočná prevádzka $22^{30} – 5^{00}$
3. Sobota, nedeľa, sviatky - všetky víkendové dni (sviatkom sa rozumejú štátne sviatky a ďalšie sviatky, ktoré sú dňami pracovného pokoja)
   a. Denná prevádzka: $6^{00} – 22^{30}$
   b. Nočná prevádzka $22^{30} – 6^{00}$

Časové rozloženie prepravnej ponuky	Pracovný deň (školský, prázdniny)	Víkendový deň
ranná špička	5^{00} – 8^{00}	6^{00} – 20^{00}
sedlo dopoludnia	8^{00} – 13^{00}	
odpoludňajšia špička	13^{00} – 17^{00}	
sedlo odpoludnia	17^{00} – 20^{00}	
večerný režim	20^{00} – 22^{30}	20^{00} – 22^{30}
nočný režim	22^{30} – 5^{00}	22^{30} – 6^{00}

Dopravné výkony sú v priebehu 24 hodín rozložené nerovnomerne na ráno, sedlo, popoludnie, večer a noc a sú prispôsobené dopytu cestujúcich po doprave, pri zachovaní základnej obslužnosti záujmového územia.

Čas prevádzky jednotlivých liniek MHD sa určuje osobitne s prihliadnutím na charakter liniek a prepravné nároky jednotlivých oblastí.

3.2 Organizácia MHD počas školských prázdnin

V období od 01. 01. 2026 – 31. 12. 2026 bude počas nižšie uvedených pracovných dní platiť prevádzkový režim **Pracovný deň – prázdniny**:

Prázdniny	Dátum/Obdobie	Počet pracovných dní
Zimné (novoročné)	2. 1. – 7. 1. 2026	3
Polročné	2. 2. 2026	1
Jarné	2. 3. – 6. 3. 2026	5
Veľkonočné	2. 4 a 7. 4. 2026	2
Letné	1. 7. – 31. 8. 2026	43
Jesenné	29. a 30. 10. 2026	2
Zimné (vianočné)	23. 12. – 30. 12. 2026	4

3.3 Štátne sviatky a sviatky, ktoré sú dňami pracovného pokoja v kalendárnom roku 2026

Dátum	Druh dňa	Typ sviatku	Názov sviatku
1. 1. 2026	štvrtok	deň pracovného pokoja	Deň vzniku Slovenskej republiky
6. 1. 2026	utorok	deň pracovného pokoja	Zjavenie Pána – Traja králi
3. 4. 2026	piatok	deň pracovného pokoja	Veľký piatok
6. 4. 2026	pondelok	deň pracovného pokoja	Veľkonočný pondelok
1. 5. 2026	piatok	deň pracovného pokoja	Sviatok práce
5. 7. 2026	nedeľa	deň pracovného pokoja	Sviatok svätého Cyrila a Metoda
29. 8. 2026	sobota	deň pracovného pokoja	Výročie Slovenského nár. povstania
1. 11. 2026	nedeľa	deň pracovného pokoja	Sviatok všetkých svätých
24. 12. 2026	štvrtok	deň pracovného pokoja	Štedrý deň
25. 12. 2026	piatok	deň pracovného pokoja	Prvý sviatok vianočný
26. 12. 2026	sobota	deň pracovného pokoja	Druhý sviatok vianočný

V dňoch pracovného pokoja premáva MHD podľa cestovného poriadku platného pre nedeľu. Na Štedrý deň večer premáva MHD v osobitnom režime.

3.4 Osobitný prevádzkový režim

3.4.1 Osobitný prevádzkový režim platí len vo vybraných dňoch roka:

- V súvislosti so Sviatkom všetkých svätých a Pamiatky zosnulých v dňoch 31.10.2026 (sobota) a 01.11. (sviatok/nedeľa) na linkách obsluhujúcich lokality mestských cintorínov a Táboriska bude zvýšená ponúkaná kapacita na linkách č. 10, 12, 19, 29, 39 formou nasadenia vozidiel s vyššou kapacitou, s ohľadom na disponibilnosť vozidlového parku.
  V dňoch 31.10. – 1.11.2026 bude na linkách 29 a 39 zvýšený počet spojov, premávajúcich v 60-minútovom intervale. Zároveň bude zriadená linka X premávajúca na trase Pod Šalgovíkom – Rusínska – Lesík Delostrelcov –Vajanského – Hlavná – Masarykova – Rusínska – Arm. Gen. Svobodu – Solivarská – Solivar Cintorín – Suvorovova – Arm. Gen. Svobodu – Pod Šalgovíkom v intervale 60 min. Navýšenie kilometrového výkonu v súvislosti so Sviatkom všetkých svätých bude 532 km.
- Doprava 24. 12. 2026 Štedrý deň (štvrtok) – cestovný poriadok podľa základného prevádzkového režimu pre NEDEĽU bude postupne ukončovaný od 17^{00} (postupné ukončenie dojazdami jednotlivých spojov). V čase 17^{00} – 22^{30} bude organizácia MHD zabezpečená nočnými linkami N1 - N2 v intervale 40 až 120 minút, na ktorý bude plynule nadväzovať štandardný nočný režim. V súvislosti so skrátením základného prevádzkového režimu pre nedeľu a skorším prechodom na nočné spoje sa zníži denný kilometrový výkon približne o 1450 km v závislosti od schválených cestovných poriadkov.
- Doprava 31. 12. 2026 Silvester (štvrtok) – cestovný poriadok podľa základného prevádzkového režimu pre SOBOTU v plnom rozsahu s výlukami premávky MHD na Hlavnej ulici v určenom čase (spravidla 22^{30} – 02^{00}).

3.4.2 Osobitný prevádzkový režim zavedený v dôsledku nedostatočných technických kapacít:

- Na základe oznámenia dopravcu s účinnosťou od 15. 01. 2024 nie sú v režime PD vykonávané vybrané spoje. V súčasnosti nie je v tomto režime realizovaných celkovo 40 spojov na linkách č.12, 17, 28, 32, 32A, 34, 35, 39 a 45 z dôvodu nedostatočného počtu štandardných autobusov. V dôsledku tohto obmedzenia sa denne najazdí o 243,5 km menej.
- Ak nepriaznivá situácia s vozidlovým parkom pretrvá až do konca kalendárneho roka 2026, celkový úbytok kilometrových výkonov oproti ročnému plánu dosiahne 46752 km.
- Plánuje sa však postupné obnovenie nevykonávaných spojov. Z tohto dôvodu sú tieto spoje zahrnuté v tabuľke „Plán výkonových parametrov liniek MHD v záujmovom území mesta Prešov“ uvedenej v bode 6.1, pričom dotknuté údaje sú označené červenou farbou.

4. ČINNOSTI V ZÁUJMOVOM ÚZEMÍ MESTA S VPLYVOM NA PREVÁDZKU MHD

Na prevádzku MHD budú mať vplyv stavebné a iné aktivity predpokladané v záujmovom území mesta Prešov v kalendárnom roku 2026. Nižšie uvedené stavebné činnosti predstavujú predpokladané stavebné aktivity, ktoré sú známe bez presného časového vymedzenia v čase spracovania materiálu. Uvedené plánované stavebné činnosti nerealizuje dopravca. Zmeny v kilometrových výkonoch pri jednotlivých aktivitách nie sú zahrnuté v RPO 2026.

Stavebné činnosti – predpoklad:

- Rekonštrukcia mosta na Šípkovej ulici,
- Rekonštrukcia mosta na ul. Jána Pavla II. (I. + II. etapa),
- Rekonštrukcia mosta na Šebastovskej ulici,
- Rekonštrukcia Solivarskej ulice,
- Modernizácia údržbovej základne trolejbusov a výstavba meniarne na Bardejovskej ulici (v areáli dopravcu),
- Rekonštrukcia mostov na Požiarnickej ulici (medzi ul. 17. novembra a Obrancov mieru),
- Rekonštrukcia mosta na Bajkalskej ulici,
- Bus-pruh Sekčovská – L. Novomeského – II. etapa, vrátane rekonštrukcie zastávky MHD L. Novomeského,
- Prestupné terminály a rekonštrukcie zastávok MHD – podľa Plánu investičnej výstavby mesta Prešov.

Na prevádzku MHD majú vplyv taktiež stavebné činnosti, ktoré zabezpečujú odstránenie porúch a havarijných stavov na komunikáciách, inžinierskych sieťach, budovách a pod. Rozsah ich vplyvu na MHD nie je možné vopred určiť. Prevádzka MHD sa operatívne upravuje v súlade s vydanými rozhodnutiami mesta Prešov alebo príslušných obcí (mesta) v záujmovom území mesta Prešov.

Zároveň je potrebné poukázať aj na ďalšie plánované stavebné projekty, ktoré v čase prípravy tohto materiálu sú v štádiu spracovania projektových dokumentácií, vydávania povolení a procesu verejného obstarávania na výber zhotoviteľa predmetných stavieb, avšak v dobe vypracovania RPO 2026 nie je známe, v ktorom kalendárnom roku alebo v akom časovom horizonte budú tieto činnosti reálne uskutočňované:

- Rekonštrukcia trolejového vedenia na Budovateľskej ulici vrátane obratiska na Budovateľskej ulici a križovatky ulíc Budovateľská – Škultétyho,
- Rekonštrukcia trolejového vedenia na Sabinovskej ulici v úseku Nám. mieru – Zlatý Bažant,
- Rekonštrukcia trolejového vedenia na uliciach Obrancov mieru a 17. novembra,
- Rekonštrukcia trolejového vedenia na uliciach Duklianska – Bardejovská – Vranovská vrátane obratiska Nižná Šebastová,
- Výstavba trolejbusovej dráhy na uliciach Kuzmányho – Rusínska a obratiska na uliciach Levočská – Clementisova,
- Vybudovanie obratiska Pod Šalgovíkom,
- Výstavba nových trakčných meniarní Solivarská, Čapajevova, Mukačevská.

Iné aktivity, vyžadujúce zmeny v organizácii prevádzky MHD:

- Kultúrno – spoločenské a športové podujatia,
- Požiadavky a podnety na úpravu a rozšírenie dopravnej obslužnosti MHD.

5. ZMENY V ORGANIZÁCII MHD V PRIEBEHU KALENDÁRNEHO ROKA 2026

V priebehu kalendárneho roka dôjde k zmene prevádzkového režimu podľa údajov uvedených v odseku 3.2, 3.3 a 3.4.

Pravidelná zmena cestovných poriadkov je plánovaná v termíne celoštátnej zmeny cestovných poriadkov, resp. k termínu zmeny cestovných poriadkov pre prímestskú autobusovú a vlakovú dopravu, ktorá sa zvyčajne realizuje v druhú decembrovú nedeľu. Pripomienky k cestovnému poriadku a požiadavky na jeho úpravu sú v priebehu roka evidované a pri príprave zmien sa posudzuje možnosť a opodstatnenosť ich zapracovania. Termín pre doručenie návrhov na zmenu je do 31. 8. 2026. Úpravy, zmeny a doplnenia cestovných poriadkov schvaľuje mesto Prešov ako objednávateľ dopravných služieb v záujmovom území mesta Prešov a príslušný správny orgán v súlade so zákonom č. 332/2023 Z. z. o verejnej osobnej doprave a o zmene a doplnení niektorých zákonov.

V prípade, ak v priebehu kalendárneho roka vznikne akákoľvek mimoriadna situácia, bude cestovný poriadok upravovaný operatívne, na základe dohody a schválenia mestom Prešov ako objednávateľom dopravných služieb v záujmovom území mesta Prešov a príslušným správnym orgánom v súlade so zákonom č. 332/2023 Z. z. o verejnej osobnej doprave a o zmene a doplnení niektorých zákonov.

5.1 Zmeny organizácie MHD z dôvodov stavebných činností v záujmovom území mesta Prešov

Organizácia MHD závisí od viacerých faktorov - termínu obmedzenia (výluky) dopravy, časového súbehu termínov viacerých stavieb, dĺžky obmedzenia (výluky), plánu organizácie výstavby jednotlivých stavieb, a pod. Možné spôsoby náhradnej dopravy sú uvedené ako modelové a pre situáciu, kedy by sa predmetná stavebná činnosť uskutočnila v záujmovom území samostatne (t. j. nie v súbehu viacerých stavieb).

Vzhľadom na rozsah služieb, prevádzkový režim a čo najefektívnejšiu náhradu poskytovaných služieb pre zabezpečenie dopravnej obslužnosti záujmového územia je nutné, aby stavebné činnosti, ktoré výrazne ovplyvňujú organizáciu MHD boli realizované v čase letných prázdnin (júl – august). V čase spracovania materiálu neboli známe presné termíny realizácie uvedených stavebných činností.

5.1.1 Rekonštrukcia mosta na Šípkovej ulici

Podľa projektovej dokumentácie sa v rámci stavebných prác pri rekonštrukcii mosta obmedzí premávka až v etape č. 2 priebehu výstavby. To znamená, že obojsmerná premávka bude vedená striedavo v jednom jazdnom pruhu. Projektantom udávaná minimálna šírka jazdného pruhu bude 3 metre, čo by malo postačovať na zachovanie prevádzky linky č. 11 v pôvodnej trase.

V etape č. 3 priebehu výstavby sa počíta s úplnou uzávierkou Suvorovovej ulice, čo si vyžiada zmenu organizácie linky č. 11 s nasledovnými dopadmi:

- Obchádzková trasa bude vedená po ulici Solivarská,

- Nebudú obojsmerne obsluhované zastávky v pôvodnej trase linky, a to: Suvorovova, Cintorín Solivar, Na brehu, Pod Hrádkom,
- Čiastočne obmedzená bude obsluha zastávky Valkovská spojmi končiacimi alebo začínajúcimi na Solivare,
- Zvýši sa obojsmerná obsluha zastávok po náhradnej trase na ulici Solivarská, a to: Múzeum Solivar, Bohúňova, Solivarská.

5.1.2 Rekonštrukcia mosta na ulici Jána Pavla II

V roku 2025 bola zahájená I. fáza rekonštrukcie mosta na ulici Jána Pavla II., ktorá si vyžiadala obojsmernú uzávierku mostného objektu. Predpokladaná doba trvania uzávierky je do konca októbra 2026. Úplná výluka dopravy počas realizácie stavebných prác má zásadný dopad na organizáciu MHD, najmä na autobusové linky č. 27, 43, školský spoj P a dočasne zriadenú linku R, ktoré v roku 2026 premávajú v režime schválených výlukových cestovných poriadkov. Uvedené výlukové kilometrické výkony sú už zahrnuté v plánovaných kilometrových výkonoch na rok 2026.

V súvislosti s plánovanou II. fázou rekonštrukcie mosta na ulici Jána Pavla II. v roku 2026, ktorá zahŕňa aj úpravu výškových pomerov v križovatke ulíc Škultétyho – 17. novembra, dôjde k úplnej uzávierke uvedenej križovatky a zároveň odstaveniu trakčného vedenia, čo znemožní prevádzku trolejbusovej dopravy. Náhradná doprava v podobe autobusových liniek alebo parciálnych trolejbusov bude zabezpečená v obmedzenom rozsahu po obchádzkových trasách, ktoré boli definované na pracovnom stretnutí dňa 10. 03. 2025. S prihliadnutím na požiadavku dopravcu uvedenú vo Vyjadrení k rekonštrukcii mosta na ulici Jána Pavla II. z 19.03.2025, evidované pod číslom 355/2025, dopravca predpokladá, že realizácia prác na uvedenej križovatke bude prebiehať výhradne počas letných prázdnin, konkrétne v mesiacoch júl a august. Tento termín umožní efektívnejšie zvládnutie výluky MHD a minimalizovanie negatívnych dopadov na cestujúcu verejnosť a dopravnú obslužnosť daného územia.

5.1.3 Rekonštrukcia mosta na Šebastovskej ulici

Úplná uzávierka sa dotkne autobusovej linky č. 13 a školských spojov A, H, J. Predbežná organizácia dopravy dotknutých liniek v súvislosti s úplnou uzávierkou:

- Školský spoj A bude skrátený po zastávku Vranovská; k ZŠ Ľubotice vozidlo príde ako školský spoj H.
- Školský spoj H bude medzi zastávkami Nová a ZŠ Ľubotice premávať cez zastávku Nižná Šebastová a ulice Limbová, Slánska, Šebastovská a Strážnická.
- Školský spoj J bude medzi zastávkami ZŠ Ľubotice a Nová premávať po uliciach Slánska, Šebastovská, Bardejovská, Kalinčiakova, Nižnianska a Vranovská.
- Linka č. 13 zabezpečuje dopravnú obslužnosť mesta Prešov a obcí Ľubotice, Vyšná Šebastová a Podhradík. Vzhľadom na zložitosť riešenia obchádzkovej trasy a potrebu zachovania dopravnej obslužnosti dotknutého územia, ako aj zabezpečenia nadväznosti na linku č. 1, sú základné obchádzkové trasy stanovené nasledovne:
    - Podhradík smer Čierny most: Herlianska, Pažica, Vranovská, Herlianska, Limbová, Slánska, Šebastovská a ďalej po základnej trase.
    - Veľká pošta smer Podhradík: v základnej trase po zastávku Strážnicka, následne cez ulice Strážnicka, Ľubotická, Slánska, Šebastovská, Bardejovská, Kalinčiakova, Nižnianska a Vranovská.

5.1.4 Rekonštrukcia Solivarskej ulice

Stavebná činnosť ovplyvní prevádzku trolejbusových liniek č. 1, 4, 8, 38, ktoré tvoria základný nosný systém dopravy v rozsahu:

- pracovný deň školský - 5 štandardných vozidiel a 15 kĺbových vozidiel,
- pracovný deň prázdniny - 4 štandardné vozidlá a 12 kĺbových vozidiel,
- víkendový deň - 2 štandardné vozidlá a 12 kĺbových vozidiel.

Obojsmerná premávka na Solivarskej ulici musí byť zachovaná. Trolejové vedenie bude presunuté do aktuálne prejazdných jazdných pruhov. Počas rekonštrukcie Solivarskej ulice dôjde k obmedzeniu trolejbusovej dopravy výlučne v čase prekládky trolejového vedenia, pričom táto prekládka musí byť realizovaná výhradne počas víkendových dní.

Pri dodržaní uvedených podmienok sa nepredpokladá zvýšenie kilometrového výkonu, dôjde len k presunu medzi trakciami. Náhrada trolejbusovej dopravy autobusovou dopravou v plnom rozsahu je možná iba počas víkendov, avšak v pracovných dňoch ju v súčasnosti vzhľadom na poddimenzovaný vozidlový park nie je možné zabezpečiť.

5.1.5 Modernizácia údržbovej základne trolejbusov a výstavba meniarne na Bardejovskej ulici

V druhej polovici kalendárneho roka 2026 sa predpokladá začiatok realizácie stavebných prác v rámci projektu „Modernizácia údržbovej základne trolejbusov a výstavba meniarne“ na Bardejovskej ulici v Ľuboticiach (v areáli dopravcu). Počas trvania stavebných prác bude dočasne využívaná náhradná vozovňa na Solivarskej ulici č. 2.

Z náhradnej vozovne bude zabezpečovaná výprava všetkých dráhových vozidiel (trolejbusov a parciálnych trolejbusov) a prevažnej časti autobusov. Zmena polohy vozovne bude mať priamy vplyv na zmenu cestovných poriadkov, keďže budú upravené výjazdy vozidiel MHD na linky a príjazdy z nich. Vplyv na celkové kilometrové výkony nie je možné v čase spracovania tohto dokumentu vyčísliť, keďže nie sú známe základné vstupné parametre, najmä termín začatia realizácie stavby a rozsah obmedzení vyplývajúcich zo stavebných prác.

5.1.6 Rekonštrukcia mostov na Požiarnickej ulici

Po mostnom objekte je vedené trolejové vedenie, pričom pripravovaná rekonštrukcia sa dotkne trolejbusových liniek č. 2, 5, 38 a autobusových liniek č. 34 a N1. Najmenší zásah do premávky MHD a zároveň aj najnižší vplyv na kilometrické výkony je predpokladaný v prípade, ak budú mosty rekonštruované ako samostatné objekty so zachovaním obojsmernej prejazdnosti aspoň jedného z nich. Takýto postup však predpokladá priebežnú úpravu a prepojenie trolejového vedenia tak, aby bolo v každej etape stavebných prác vedené výhradne cez prejazdný most.

5.1.7 Rekonštrukcia mosta na Bajkalskej ulici

Po tomto moste je vedené trolejové vedenie. Rekonštrukcia sa dotkne technologických jázd trolejbusov (výjazdov na Sídlisko III a príjazdov do vozovne) začínajúcich a končiacich na obratisku Sídlisko III pre trolejbusové linky č. 4, 5, 8, 38 a pravidelných spojov trolejbusovej linky č. 5, autobusovej linky č. 12, 43 a školského spoja S. Počas stavebných prác na moste sa

počíta s úplnou uzávierkou mosta pre trolejbusy. Obojsmerná premávka pre autobusovú prepravu bude čiastočne obmedzená, a to vedená striedavo v jednom jazdnom pruhu.

Vplyv uzávierky na pravidelné spoje trolejbusovej linky č. 5:

Za predpokladu, že nebudú súčasne iné uzávierky, na linku č. 2/5 a č. 5/2 bude denne vypravený jeden parciálny trolejbus, ktorý zabezpečí obsluhu zastávok Bajkalská a Veterinárna nemocnica ako spoj linky č. 5 v intervale 120 minút. Ostatné spoje linky č. 2/5 a č. 5/2 budú vykonávané trolejbusmi, ktoré budú odklonené z ulice Bajkalskej na obratisko Dúbrava.

Vplyv uzávierky na technologické jazdy liniek č. 4, 8, 38:

Trolejbusové výjazdy z vozovne na Sídlisko III a následné príjazdy zo Sídliska III do vozovne budú realizované po obchádzkovej trase cez ulice Hlavná, Škultétyho, 17. novembra, Obrancov mieru, Clementisova, Volgogradská a Prostějovská. Pri súčasne platnom cestovnom poriadku sa to týka 27 technologických jázd v školských pracovných dňoch a 21 technologických jázd v prázdninovom a víkendovom režime.

Tu je potrebné zdôrazniť, že rekonštrukcia mostov Jána Pavla II. (vrátane cestnej komunikácie na uliciach Škultétyho a 17. novembra), Požiarnická a Bajkalská sa nemôže realizovať súčasne v rovnakom časovom období z dôvodu znemožnenia realizácie technologických jázd trolejbusov z a na Sídlisko III.

5.1.8 Bus-pruh Sekčovská – L. Novomeského – II. etapa, vrátane rekonštrukcie zastávky MHD L. Novomeského

Je plánovaná zmena organizácie dopravy – stavebné úpravy a úprava dopravného značenia vytvorením vyhradeného jazdného pruhu na Sekčovskej ulici a ulici L. Novomeského pre vozidlá mestskej hromadnej dopravy, záchranných zložiek, taxi a ostatné vozidlá verejnej dopravy. II. etapa výstavby sa týka úprav v križovatke ulíc Sekčovská a L. Novomeského, časti ulice L. Novomeského v smere ku križovatke s ulicou Arm. Gen. Svobodu a dvoch nástupísk zastávky MHD L. Novomeského.

Stavbou bude obmedzená premávka trolejbusovej linky 4 v úseku od zastávky MHD M. Benku po konečnú zastávku Pod Šalgovíkom. Linku je možné v čase realizácie stavby presmerovať na Sibírsku ulicu a lokalitu L. Novomeského - Sekčovská - Pod Šalgovíkom obsluhovať náhradou autobusovou alebo parciálnou trolejbusovou dopravou.

5.1.9 Prestupné terminály a rekonštrukcie zastávok MHD – podľa Plánu investičnej výstavby mesta Prešov

Pri stavbe predpokladáme len minimálny zásah do organizácie MHD, napr. jednorazovo cez víkend, kvôli realizácii niektorých činností (asfaltovanie komunikácie a pod.).

5.2 Zmeny z dôvodu kultúrnych, spoločenských a športových podujatí.

Organizáciu MHD v priebehu kalendárneho roka budú ovplyvňovať podujatia, ktoré sa konajú každoročne (uskutočnili sa min. v rokoch 2023, 2024, 2025):

- Apríl - bežecké podujatie „Stars RUN“ - výluka premávky na Hlavnej ulici vo víkendovom dni v podvečerných hodinách;

- Jún – kultúrne podujatie „Dobrý festival“ (piatok – nedeľa) - posilnenie dopravy v lokalite Žel. stanica, sídlisko Sekčov, Šváby, Delňa samostatnou linkou „X“; predpokladá sa deľba navýšených výkonov medzi organizátora a mesto Prešov;
- Jún – kultúrne podujatie „Trojičný jarmok a Dni mesta Prešov“ – plánovaná výluka premávky na Hlavnej ulici v dňoch 05.06. – 07.06.2026 nepretržite;
- Júl – cyklistické preteky „TOUR DE PREŠOV“ – výluka premávky na Hlavnej ulici vo víkendovom dni v čase cca 8.00-16.00 hod;
- August – kultúrne podujatie „Helfest“ (sobota, nedela) - posilnenie dopravy v lokalite Žel. stanica, sídlisko Sekčov, Šváby, Delňa samostatnou linkou „X“; predpokladá sa deľba navýšených výkonov medzi organizátora a mesto Prešov;
- September – kultúrne podujatie „Deň soli“ na Solivare – posilnenie linky 1 vo víkendovom dni;
- September – kultúrne podujatie „Letecké dni“ na letisku – predĺženie linky 1, intervalové a kapacitné posilnenie linky 1 vo víkendových dňoch;
- September – podujatie „Európsky týždeň mobility“ v dňoch 16.09. – 22.09. Aktivity budú uskutočňované podľa rozsahu zapojenia sa mesta Prešov;
- December - bežecké podujatie „MIKULÁŠSKY BEH“ – výluka premávky na Hlavnej ulici vo víkendovom dni v čase cca 16.00-20.00 hod;
- December – „Štefanská zábava“ - výluka premávky na Hlavnej ulici vo víkendovom dni v čase cca 19.00-22.00 hod;
- December - kultúrne podujatie „Silvester 2026“ - výluka premávky na Hlavnej ulici 31.12. – 01.01. v čase cca 22:30-02:00 hod.

Uvedené časy výluk sú orientačné, presné termíny podujatí vyplynú z rozhodnutí mesta Prešov.

5.3 Požiadavky a podnety na úpravu a rozšírenie dopravnej obslužnosti MHD

V priebehu kalendárneho roka 2025 boli zo strany mesta Prešov, dotknutých mestských častí, a ich obyvateľov vznesené viaceré požiadavky a podnety smerujúce k rozšíreniu dopravnej obslužnosti mestskou hromadnou dopravou do nových, resp. rozvojových území mesta. Tieto iniciatívy reflektujú jednak postupný urbanistický rozvoj okrajových častí, ako aj snahu zabezpečiť obyvateľom týchto lokalít štandardný prístup k službám verejnej osobnej dopravy.

V nadväznosti na uvedené, mesto Prešov pre kalendárny rok 2026 vznieslo požiadavku na zavedenie dopravnej obslužnosti linkami MHD do týchto lokalít:

- Tichá dolina,
- Záhradné sady.

Zavedenie pravidelnej obsluhy MHD do uvedených území bude mať priamy vplyv na zvýšenie celkového rozsahu kilometrových výkonov a potrebu nasadenia dodatočných vozidiel a vodičov. Aj keď si dopravca uvedomuje potrebu zavedenia základnej dopravnej obslužnosti týchto lokalít prostredníctvom liniek MHD, vzhľadom na aktuálne kapacitné možnosti dopravcu nie je v súčasnosti možné určiť presný rozsah ani termín začatia ich obsluhy tak, aby nebol ohrozený existujúci rozsah dopravných výkonov v ostatných častiach mesta. Z tohto dôvodu nie je možné ani presne vyčísliť očakávané kilometrové výkony spojené so zavedením MHD do spomínaných lokalít.

5.4 Organizácia MHD pri výlukách cestnej premávky z Hlavnej ulice

Spôsob organizácie premávky MHD pri výlukách cestnej premávky z Hlavnej ulice v čase konania podujatí závisí od typu prevádzkového dňa a času výluky.

Prevádzkové podmienky a možnosti zabezpečenia MHD počas výluky premávky na Hlavnej ulici predstavujú:

- Základná obchádzková trasa vedie cez ulice ...Remscheidská – Okružná – Štefánikova...
- Je potrebná náhrada nosnej trolejbusovej dopravy za autobusovú dopravu v plnom rozsahu. V pracovný deň (školský, prázdninový) je náhrada v plnom rozsahu možná po osemnástej hodine. Počas víkendových dní je náhrada v plnom rozsahu možná celodenne. Náhrady trolejbusovej dopravy za autobusovú nie sú vhodné a žiadúce, a je nutné ich minimalizovať, vzhľadom na sledovaný merateľný ukazovateľ - počet prepravených osôb trolejbusmi zakúpenými z fondov EÚ OPII v rámci projektu „Modernizácia vozového parku trolejbusov v Prešove“.

Možnosti zabezpečenia výluk:

- odklonom autobusových liniek na základnú obchádzkovú trasu;
- odklonom trolejbusových liniek č. 4 a 8 na trasu cez ul. Obrancov mieru - 17. novembra – Škultétyho (v trase linky č. 38);
- náhradou trolejbusovej dopravy na linkách č. 1, 2, 5, 7 za autobusovú a ich odklonom po základnej obchádzkovej trase (v závislosti od disponibilných vozidiel);
- zriadením autobusovej kyvadlovej dopravy na trase Železničná stanica – Masarykova – Štefánikova – Okružná – Remscheidská – Levočská – Clementisova a späť.

5.4.1 Výluka dopravy z Hlavnej ulice počas kultúrneho podujatia „Trojičný jarmok a Dni mesta Prešov“

V kalendárnom roku 2026, rovnako ako v predchádzajúcom kalendárnom roku, je plánované kultúrne podujatie „Trojičný jarmok a Dni mesta Prešov“ s nepretržitou uzávierkou Hlavnej ulice v termíne od 05. 06. 2026 od 08:30 hod. do 08. 06. 2026 do 04:00 hod.

Organizácia premávky MHD pri nepretržitej výluke Hlavnej ulice s rozdelením podľa typu prevádzkového dňa bude predstavovať:

<u>Dňa 05. 06. 2026 – pracovný deň školský od 8:30 hod.</u>

Súčasná kapacita a štruktúra vozidlového parku dopravcu neumožňuje zabezpečiť úplnú náhradu trolejbusovej dopravy autobusmi po štandardnej obchádzkovej trase vedenej cez Okružnú ulicu. Prevádzka náhradnej dopravy bude preto realizovaná v rozsahu, ktorý bude priamo závislý od aktuálnej disponibilnej kapacity vozidiel, najmä autobusov a parciálnych trolejbusov.

<u>V dňoch 06. 06. – 07. 06. 2026 – víkendové dni</u> - štandardný výlukový režim podľa bodu 5.4

6. PLÁN VÝKONOV DOPRAVNÝCH SLUŽIEB NA KALENDÁRNY ROK 2026

Plán výkonov dopravných služieb v záujmovom území mesta Prešov na kalendárny rok 2026 je spracovaný v súlade s článkom 3. Podmienky poskytovania dopravných služieb, bodom 3.6. Rámcovej zmluvy o službách vo verejnom záujme a zabezpečení mestskej hromadnej dopravy osôb v meste Prešov na roky 2017-2026 zo dňa 22. 12. 2016 v znení dodatkov uzatvorenej s mestom Prešov a v súlade so schváleným cestovným poriadkom s platnosťou od 01. 01. 2026.

Plán výkonov je uvedený pre autobusovú, elektrobusovú a trolejbusovú trakciu. Predpokladaný podiel výkonu parciálnymi trolejbusmi je na úrovni 20% z výkonov trolejbusovej trakcie.

6.1 Celkové plánované kilometrové výkony MHD v záujmovom území mesta Prešov na kalendárny rok 2026

Plánované celkové kilometrové výkony v km:

Typ dňa	Pracovný deň školský	Pracovný deň prázdniny	Sobota, Nedeľa, Sviatok	Spolu
počet dní	192	61	112	365
CELKOM MHD km	2 889 216,0	809 836,0	953 232,0	4 652 284,0
MHD autobusy	1 382 400,0	402 600,0	403 200,0	2 188 200,0
MHD elektrobusy	124 416,0	29 036,0	57 232,0	210 684,0
MHD trolejbusy	1 382 400,0	378 200,0	492 800,0	2 253 400,0
MHD pre Prešov	2 429 702,4	687 823,8	832 742,4	3 950 268,6
MHD pre Veľký Šariš a ostatné obce	442 444,8	116 589,3	115 830,4	674 864,5
MHD iné zmluvy	17 068,8	5 422,9	4 659,2	27 150,9
Objednávky				7 000,0
MHD + objednávky				4 659 284,0

Plánované denné výkony v km:

Trakcia / Typ dňa	Pracovný deň školský	Pracovný deň prázdniny	Sobota, Nedeľa, Sviatok
Autobusy	7 200	6600	3 600
Elektrobusy	648	476	511
Trolejbusy	7 200	6 200	4 400
Spolu	15 048	13 276	8 511

Plán výpravy vozidiel MHD (počet vozidiel):

Výprava vozidiel	Pracovný deň školský	Pracovný deň prázdniny	Sobota, Nedeľa, Sviatok
Autobusy	36	32	14
midi/štandard/kĺbový	1/21/14	1/21/10	2/9/3
Elektrobusy	5	4	4
midi	5	4	4
Trolejbusy	33	26	17
midi/štandard/kĺbový	0/13/20	0/11/15	0/5/12
Spolu	74	62	35
midi/štandard/kĺbový	6/34/34	5/32/25	6/14/15

Plánované dopravné ukazovatele:

Dopravné ukazovatele MHD	
Dĺžka siete v km	131
Dĺžka liniek v km	371
Počet vypravovaných liniek	42
z toho Denné linky	40
Nočné linky	2

(* *Pozn. skupina školských spojov je vedená ako jedna linka)*

Plán výkonových parametrov liniek MHD v záujmovom území mesta Prešov:

linka	Trasa linky (konečné zastávky)	Počet spojov			Denné výkony [km]		
		PD	PPD	SO, NE, SV.	PD	PPD	SO, NE, SV.
1	ŠEBASTOVÁ-SOLIVAR	121	105	70	1 120	990	640
2	BUDOVATEĽSKÁ-OBRANCOV MIERU	65	65	33	300	300	158
4	SÍDLISKO III-POD ŠALGOVÍKOM	112	104	95	1 170	1 082	964
5	OBRANCOV MIERU-BAJKALSKÁ/DÚB.	63	66	35	455	470	255
7	ŠIRPO-BUDOVATEĽSKÁ	46	46	12	300	300	50
8	SÍDLISKO III-SIBÍRSKA	114	106	98	1 213	1 127	1 022
10	SIBÍRSKA-NEMOCNICA-SIBÍRSKA	32	32	18	271	271	145
11	NA RÚRKACH - VEĽKÁ POŠTA	34	34	24	230	224	160
12	SIBÍRSKA -ŠIDLOVSKÁ	30	19	15	425	262	229
13	V.POŠTA-V.ŠEBASTOVÁ-PODHRADÍK	33	27	17	428	340	210
14	KANAŠ-ZÁBORSKÉ	53	46	29	660	575	334
15	ZA KALVÁRIOU-NEMOCNICA	34	34	20	220	220	128
17	SÍDLISKO III-ŠIRPO	7	4	0	61	34	0
18	DJZ-CEMJATA-BZENOV	36	36	30	377	377	243
19	SOLIVAR-NEMOCNICA	30	30	14	268	268	123
21	FINTICE- TROJICA	51	42	22	474	400	207
22	ŠIDLOVEC-ŠALGOVÍK-TERIAKOVCE	72	60	41	648	540	376
23	MALÝ ŠARIŠ - TROJICA	50	42	20	400	335	151
24	OBR.MIERU-KOLLÁROVA-HANISKA	28	28	18	220	190	109
26	VEĽKÁ POŠTA - SPINEA - Č.MOST	12	12	6	66	66	33
27	TERCHOVSKÁ-HVIEZDNA	31	31	14	238	238	110
28	DELŇA-ĽUBOTICE	54	43	33	528	420	377
29	SÍDLISKO III-NEMOCNICA	29	28	16	200	191	109
30	ŽEL.STANICA-JIL-BUD-ŽEL.STANICA	11	11	1	40	40	2
32	OKRUŽNÁ-TROJICA-SIBÍRSKA	46	22	14	253	120	57
32A	SIBÍRSKA-OKRUŽNÁ	28	14	0	115	60	0
33	DELŇA-ŠIRPO	15	14	5	117	112	32
34	SÍDLISKO III-POD ŠALGOVÍKOM	27	27	0	330	330	0
35	DELŇA-ŠIRPO	3	3	0	33	33	0
36	TROJICA - POD ŠALGOVÍKOM	26	19	5	122	82	16
37	ŽEL.STANICA-N.ŠEBASTOVÁ	3	3	0	32	32	0
38	SÍDLISKO III-SIBÍRSKA	112	104	96	1 196	1 106	999
39	SÍDLISKO III-ŠVÁBSKA	48	38	16	397	310	125
41	SURDOK-VEĽKÁ POŠTA	34	32	16	210	195	98
42	VEĽKÁ POŠTA - BORKÚT	14	14	14	75	75	75
43	ŽEL.STANICA-KOLLÁR.-NEM.-KPT.N.	3	3	0	43	43	0
44	V.POŠTA - SOLIVAR - DULOVA VES	15	15	2	113	113	7
45	DELŇA-VEĽKÝ ŠARIŠ	57	48	33	851	718	477
46	RUSKÁ NOVÁ VES-VEĽKÁ POŠTA	28	26	16	255	225	136
N1	SÍDLISKO III - SOLIVAR - POD ŠALG.	9	9	10	118	118	138
N2	N.ŠEBASTOVÁ-SIBÍRSKA-SÍDLISKO III	10	10	11	144	144	166
ZL	Zálohová linka	0	0	0	200	200	50
SK	školské spoje	14	0	0	132	0	0
Celkom za MHD		**1 640**	**1 452**	**919**	**15 048**	**13 276**	**8 511**

PD – pracovný deň so školským vyučovaním SO – Sobota, NE – Nedeľa

PPD – prázdninový pracovný deň SV - Sviatok

6.2 Plánované kilometrové výkony MHD pre mesto Veľký Šariš a jednotlivé obce v záujmovom území mesta Prešov na kalendárny rok 2026

Plánované celkové kilometrové výkony v km:

Obec	prac. deň školský	sobota	nedeľa sviatok	prac. deň prázdniny	Spolu
	192	51	61	61	365
Bzenov	18 432,0	0,0	0,0	5 856,0	**24 288,0**
Dulova Ves	16 742,4	0,0	0,0	4 770,2	**21 512,6**
Fintice	46 790,4	5 610,0	6 710,0	12 200,0	**71 310,4**
Haniska	15 321,6	2 386,8	2 854,8	4 440,8	**25 004,0**
Ľubotice	62 956,8	9 506,4	11 370,4	15 512,3	**99 345,9**
Malý Šariš	43 948,8	4 335,0	5 185,0	11 705,9	**65 174,7**
Podhradík	7 065,6	856,8	1 024,8	1 878,8	**10 826,0**
Ruská Nová Ves	28 492,8	4 324,8	5 172,8	8 405,8	**46 396,2**
Teriakovce	18 624,0	1 530,0	1 830,0	4 392,0	**26 376,0**
Veľký Šariš + Kanaš	125 414,4	18 349,8	21 947,8	32 275,1	**197 987,1**
Vyšná Šebastová	32 448,0	3 549,6	4 245,6	8 515,6	**48 758,8**
Záborské	26 208,0	2 295,0	2 745,0	6 636,8	**37 884,8**
SPOLU	**442 444,8**	**52 744,2**	**63 086,2**	**116 589,3**	**674 864,5**

Plánované denné kilometrové výkony v km:

DENNÉ VÝKONY	prac. deň školský	sobota	nedeľa sviatok	prac. deň prázdniny
Bzenov	96,0	0,0	0,0	96,0
Dulova Ves	87,2	0,0	0,0	78,2
Fintice	243,7	110,0	110,0	200,0
Haniska	79,8	46,8	46,8	72,8
Ľubotice	327,9	186,4	186,4	254,3
Malý Šariš	228,9	85,0	85,0	191,9
Podhradík	36,8	16,8	16,8	30,8
Ruská Nová Ves	148,4	84,8	84,8	137,8
Teriakovce	97,0	30,0	30,0	72,0
Veľký Šariš+Kanaš	653,2	359,8	359,8	529,1
Vyšná Šebastová	169,0	69,6	69,6	139,6
Záborské	136,5	45,0	45,0	108,8
SPOLU	**2 304,4**	**1 034,2**	**1 034,2**	**1 911,3**

Plánované výkony mestskej hromadnej dopravy pre obec DULOVA VES - rok 2026

Obec Dulova Ves je obsluhovaná linkami č. 11 a 44.

DENNÉ VÝKONY	prac. deň školský	sobota	nedeľa sviatok	prac. deň prázdniny
Počet spojov za deň:				
trasa I.	10	0	0	9
trasa II.	10	0	0	9
spolu	20	0	0	18
Denný výkon v km:				
trasa I.	31,0	0,0	0,0	27,9
trasa II.	31,0	0,0	0,0	27,9
Denný výkon na území obce (obec-hraničná z.)	**62,0**	**0,0**	**0,0**	**55,8**
Počet spojov za deň - trasa III.	14	0	0	14
trasa IV.	6	0	0	4
Denný výkon v km:				
trasa III + IV.	25,2	0,0	0,0	22,4
Denný celkový výkon	**87,2**	**0,0**	**0,0**	**78,2**

Jednotkové vzdialenosti v [km]:

Hraničná zastávka - obec

trasa I. zast. Zlatobanská - Dulova Ves 3,1 km

trasa II. Dulova Ves - Zlatobanská 3,1 km

Uzlová zastávka - hraničná zastávka

trasa III. (L44) 50% vzdialenosti medzi zastávkami L. Novomeského - Zlatobanská 1,2 km

trasa IV. (L11) 50% vzdialenosti medzi zastávkami M.Benku - Zlatobanská 1,4 km

na jednej obrátke L11 sa obec podieľa 9,0 km.

na jednej obrátke L44 sa obec podieľa 8,6 km.

Rok 2026	prac. deň školský	sobota	nedeľa sviatok	prac. deň prázdniny		SPOLU výkon v [km]
Počet dní	192	51	61	61		365
Celkový výkon za rok 2026	16 742,4	0,0	0,0	4 770,2		**21 512,6**

z toho

							podiel
v obci	11 904,0	0,0	0,0	3 403,8		**15 307,8**	71,2%
v Prešove	4 838,4	0,0	0,0	1 366,4		**6 204,8**	28,8%

Poznámka: v obci : 100 % vzdialenosti hraničná zastávka - obec - hraničná zastávka
v Prešove : 50 % vzdialenosti uzlová zastávka - hraničná zastávka - uzlová zastávka

7. INDIKATÍVNY VÝHĽAD DOPRAVNÝCH SLUŽIEB V ZÁUJMOVOM ÚZEMÍ MESTA PREŠOV NA KALENDÁRNE ROKY 2027 A 2028

Výhľad kilometrových výkonov je zostavený na úrovni denných výkonov MHD v kalendárnom roku 2026, bez zohľadnenia prípadných výluk v prevádzke. Rozdiel vo výkonoch je daný štruktúrou prevádzkových dní v rámci príslušného kalendárneho roka.

Celkové kilometrové výkony – výhľad na kalendárny rok 2027:

Typ dňa	Pracovný deň školský	Pracovný deň prázdniny	Sobota, Nedeľa, sv.	Spolu
počet dní	190	62	113	365
CELKOM MHD km	2 859 120,0	823 112,0	961 743,0	4 643 975,0
MHD autobusy	1 368 000,0	409 200,0	406 800,0	2 184 000,0
MHD elektrobusy	123 120,0	29 512,0	57 743,0	210 375,0
MHD trolejbusy	1 368 000,0	384 400,0	497 200,0	2 249 600,0
MHD pre Prešov	2 404 393,0	699 100,0	840 178,0	3 943 671,0
MHD pre obce	437 836,0	118 500,6	116 864,6	673 201,2
MHD iné zmluvy	16 891,0	5 511,8	4 700,8	27 103,6
Objednávky				7000,0
MHD + objednávky				4 650 975,0

Celkové kilometrové výkony – výhľad na kalendárny rok 2028:

Typ dňa	Pracovný deň školský	Pracovný deň prázdniny	Sobota, Nedeľa, sv.	Spolu
počet dní	190	59	117	366
CELKOM MHD km	2 859 120,0	783 284,0	995 787,0	4 638 191,0
MHD autobusy	1 368 000,0	389 400,0	421 200,0	2 178 600,0
MHD elektrobusy	123 120,0	28 084,0	59 787,0	210 991,0
MHD trolejbusy	1 368 000,0	365 800,0	514 800,0	2 248 600,0
MHD pre Prešov	2 404 393,0	665 272,2	869 918,4	3 939 583,6
MHD pre obce	437 836,0	112 766,7	121 001,4	671 604,1
MHD iné zmluvy	16 891,0	5 245,1	4 867,2	27 003,3
Objednávky				7000,0
MHD + objednávky				4 645 191,0

8. Prílohy RPO 2026:

8.1 Charakteristika liniek MHD č. 11, 44

8.2 Sieť denných liniek MHD – stav od 30. 06. 2025

8.1 Charakteristika liniek MHD č. 11, 44

Linka č. 070011

Základná trasa: **NA RÚRKACH** – Levočská – Hlavná – **Veľká pošta –** Kuzmányho – Rusínska – Eperia – Arm. Gen. Svobodu – Suvorovova – Pod hrádkom – Zlatobanská **-SOLIVAR (Dulova Ves)** a späť.

Alternatívna trasa.: Vybrané spoje premávajú do obce Dulova Ves

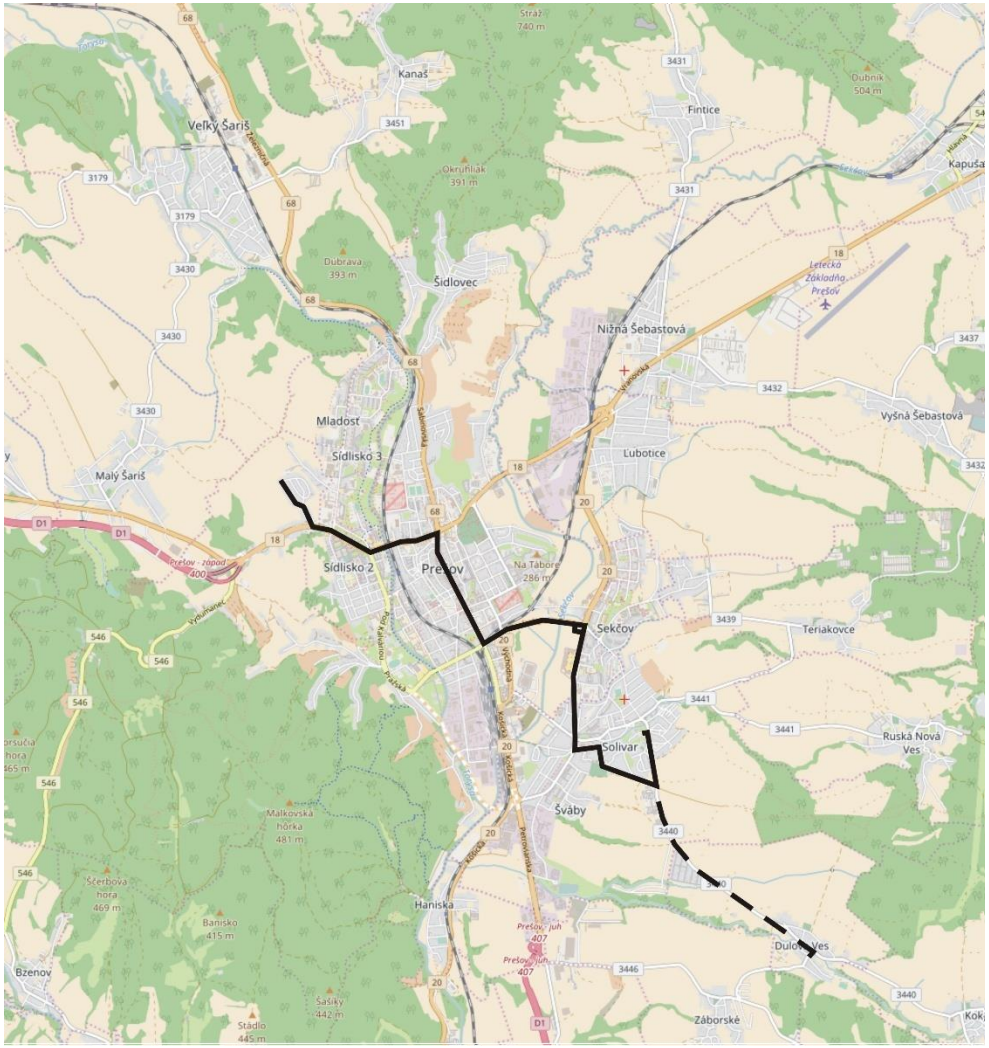

Základné parametre	Smer TAM	Smer SPÄŤ	Spolu
Dĺžka trasy (km)	9,3	9,3	18,6
Počet zastávok	20	20	40
Jazdný čas (min)	27	27	52

Obsluhované zastávky, chronometráž trasy

Smer TAM		Smer SPÄŤ	
	Dulova Ves	0'	**Na Rúrkach**
	Dulova Ves – kostol *	1'	Jána Bereša *
	Vlčie doly *	2'	Rázcestie Rúrky *
	Zlatobanská *	4'	Levočská
- -	- - - - - - - - - - - - - - - -	6'	Poliklinika
0'	**Solivar**	8'	Trojica
1'	Valkovská *	10'	Na Hlavnej
2'	Pod Hrádkom *	12'	Veľká pošta
3'	Na brehu *	13'	Čierny most
4'	Cintorín Solivar *	16'	Rusínska *
5'	Suvorovova *	17'	Eperia
7'	Lesnícka	18'	Martina Benku
8'	Pavla Horova	19'	Pavla Horova
9'	Martina Benku	20'	Lesnícka
11'	Rusínska *	22'	Suvorovova *
12'	Hobby Park *	23'	Cintorín Solivar *
14'	Čierny most	24'	Na brehu *
16'	Divadlo Jonáša Záborského	25'	Pod Hrádkom *
17'	Na Hlavnej	26'	Valkovská *
19'	Trojica	27'	**Solivar**
21'	Poliklinika	- -	- - - - - - - - - - - - - - - -
23'	Levočská	26'	Zlatobanská *
25'	Rázcestie Rúrky *	28'	Vlčie doly *
26'	Jána Bereša *	30'	Dulova Ves – kostol *
27'	**Na Rúrkach**	31'	Dulova Ves

Výkonnostné parametre	Typ prevádzkového dňa		
	PD	PPD	VD
Počet spojov	34	34	24
Výprava (počet vozidiel)	1	1	1
Denné výkony (km)	230	224	160
Interval spojov (min) @	60/120	60/120	120

Vysvetlivky: PD - pracovný deň, PPD – prázdninový pracovný deň,
VD - víkendový deň (sobota, nedeľa, št. sviatok),
* zastávka na znamenie, § - II. tarifné pásmo
@ v úseku Veľká pošta – Solivar – DJZ celotýždenný interval 120 minút.

Linka 070011

Odchody zo zastávky **Solivar**

smer **Na Rúrkach**

min.	zastávka	pásmo
0'	Solivar	1
1'	*Valkovská	1
2'	*Pod Hrádkom	1
3'	*Na brehu	1
4'	*Cintorín Solivar	1
5'	*Suvorovova	1
7'	Lesnícka	1
8'	Pavla Horova	1
9'	Martina Benku	1
11'	*Rusínska	1
12'	*Hobby park	1
14'	Čierny most	1
16'	Divadlo J.Záborského	1
17'	Na Hlavnej	1
19'	Trojica	1
21'	Poliklinika	1
23'	Levočská	1
25'	*Rázcestie Rúrky	1
26'	*Jána Bereša	1
27'	Na Rúrkach	1

h.	pracovný deň-školský	pracovný deň-prázdniny	sobota,nedeľa,sviatok
4			
5	12P 58A	12P	17P
6	46U	06A 50	
7			05
8	16A	16A	
9	00 56U	00 56U	05
10			
11	00	00	05
12	16A	16A	
13	00	00	05
14	16A	16A	
15	00	00	05
16	16A	16A	
17	00	00	05
18	16A	16A	
19	01U	01U	05
20	21A	21A	
21			
22	21AC	21AC	21AC

VYSVETLIVKY: * zastávka na znamenie; P zo zastávky Poliklinika; Tolerancia odchodov +-2min.
A z DJZ; C ďalej ako linka 23 do M. Šariša; U z Dulovej Vsi (Pod Hr.+6´) Platnosť od 1.1.2026

Linka 070011

Odchody zo zastávky **Na Rúrkach**

smer **Solivar / Dulova Ves**

min.	zastávka	pásmo
0'	Na Rúrkach	1
1'	*Jána Bereša	1
2'	*Rázcestie Rúrky	1
4'	Levočská	1
6'	Poliklinika	1
8'	Trojica	1
10'	Na Hlavnej	1
12'	Veľká pošta	1
13'	Čierny most	1
16'	*Rusínska	1
17'	Eperia	1
18'	Martina Benku	1
19'	Pavla Horova	1
20'	Lesnícka	1
22'	*Suvorovova	1
23'	*Cintorín Solivar	1
24'	*Na brehu	1
25'	*Pod Hrádkom	1
26'	*Valkovská	1
27'	Solivar	1
26'	*Zlatobanská	1
28'	*Vlčie doly	2
30'	*Dulova Ves - kostol	2
31'	Dulova Ves	2

h.	pracovný deň-školský	pracovný deň-prázdniny	sobota,nedeľa,sviatok
4			
5	20V	20V	25V
6	12D	20S	21LS
7	20V	20V	35V
8	30S	30S	21LS
9	30H 32BD	30H 32BD	35V
10	30S	30S	21LS
11	30V	30V	35V
12	30S	30S	21LS
13	30V	30V	35V
14	30S	30S	21LS
15	30V	30V	35V
16	30S	30S	21LS
17	30V	30V	35V
18	30D	30D	21LS
19	35V	35V	35V
20	35V	35V	

VYSVETLIVKY: * zastávka na znamenie; L zo zast. Levočská
V po Veľkú poštu; S po Solivar; D vynechá zast. Valkovská a Solivar
B z Veľkej pošty Tolerancia odchodov +-2min.
H po zast. Na Hlavnej Platnosť od 1.1.2026

Linka č. 070044

Základná trasa: **VEĽKÁ POŠTA** – Masarykova – Kuzmányho – Rusínska – Eperia - Laca Novomeského – Kysucká - Solivar – Zlatobanská – Vlčie doly – **Dulova Ves** a späť (bez zachádzky Eperia)

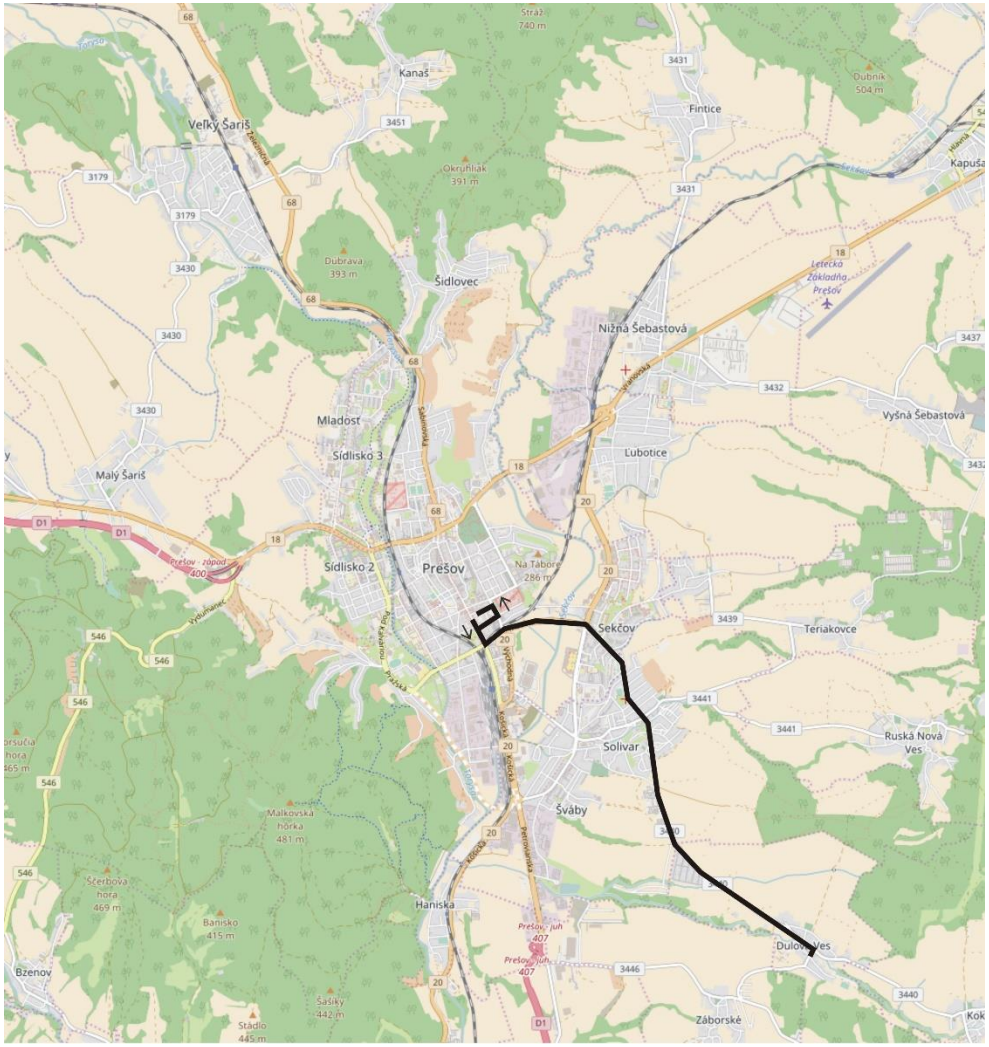

Základné parametre	Smer TAM	Smer SPÄŤ	Spolu
Dĺžka trasy (km)	7,8	7,7	15,5
Počet zastávok	13	12	25
Jazdný čas (min)	18	17	35

Obsluhované zastávky, chronometráž trasy

Smer TAM			Smer SPÄŤ		
0'	**Veľká pošta**		0'	**Dulova Ves**	§
1'	Čierny most		1'	Dulova Ves – kostol *	§
4'	Rusínska *		3'	Vlčie Doly *	§
5'	Eperia		6'	Valkovská *	
8'	L. Novomeského		7'	Solivar	
9'	Kysucká *		8'	Kukučínova *	
10'	Kukučínova *		9'	Kysucká *	
11'	Solivar		10'	L. Novomeského	
12'	Valkovská *		12'	Rusínska *	
13'	Zlatobanská *		13'	Hobby park *	
15'	Vlčie doly *	§	15'	Čierny most	
17'	Dulova Ves – kostol *	§	17'	**Kpt. Nálepku ***	
18'	**Dulova Ves**	§			

Výkonnostné parametre	Typ prevádzkového dňa		
	PD	PPD	VD
Počet spojov	15	15	2
Výprava (počet vozidiel)	1	1	0 #
Denné výkony (km)	113	113	7
Interval spojov (min)	60/-	60/-	prejazd

Vysvetlivky: PD - pracovný deň, PPD – prázdninový pracovný deň,
VD - víkendový deň (sobota, nedeľa, št. sviatok),
* zastávka na znamenie, § - II. tarifné pásmo
@ - vybrané spoje sú vykonávané midibusom;
# - spoje vykonávajú vozidlá iných liniek.

Linka 070044

Odchody zo zastávky **Veľká pošta**
smer **Dulova Ves**

min.	zastávka	pásmo
0'	Veľká pošta	1
1'	Čierny most	1
4'	*Rusínska	1
5'	Eperia	1
8'	L. Novomeského	1
9'	*Kysucká	1
10'	*Kukučínova	1
11'	Solivar	1
12'	*Valkovská	1
13'	*Zlatobanská	1
15'	*Vlčie doly	2
17'	*Dulova Ves - kostol	2
18'	Dulova Ves	2

h.	pracovný deň-školský	pracovný deň-prázdniny	sobota,nedeľa,sviatok
4			
5			
6	02A	02A	
7	02A	02A	
8			
9			
10			
11			
12			
13	05	05	
14	05	05	
15	05	05	
16	05	05	
17	05	05	
18			
19			
20			
21			
22			

VYSVETLIVKY:
* zastávka na znamenie
A neobsluhuje zastávku Eperia (jazdný čas -2 min.)

Tolerancia odchodov +-2min.
Platnosť od 1.1.2026

Linka 070044

Odchody zo zastávky **Dulova Ves**
smer **Kpt. Nálepku**

min.	zastávka	pásmo
0'	Dulova Ves	2
1'	*Dulova Ves - kostol	2
3'	*Vlčie doly	2
6'	*Valkovská	1
7'	Solivar	1
8'	*Kukučínova	1
9'	*Kysucká	1
10'	L. Novomeského	1
12'	*Rusínska	1
13'	*Hobby park	1
15'	Čierny most	1
17'	*Kpt. Nálepku	1

h.	pracovný deň-školský	pracovný deň-prázdniny	sobota,nedeľa,sviatok
4			
5	32CBE	32CBE	
6	20	20	
7	20CD	20C	
8			
9			
10			
11			
12			40CDE
13	30	30	
14	30C	30C	
15	30	30	
16	30	30	40CDE
17	30C	30C	
18			
19			
20			
21			
22			

VYSVETLIVKY:
* zastávka na znamenie
C po Čierny most; B ďalej ako linka 41; D ďalej ako linka 18
E zo zastávky Solivar (nástupisko na otočke)

Tolerancia odchodov +-2min.
Platnosť od 1.1.2026
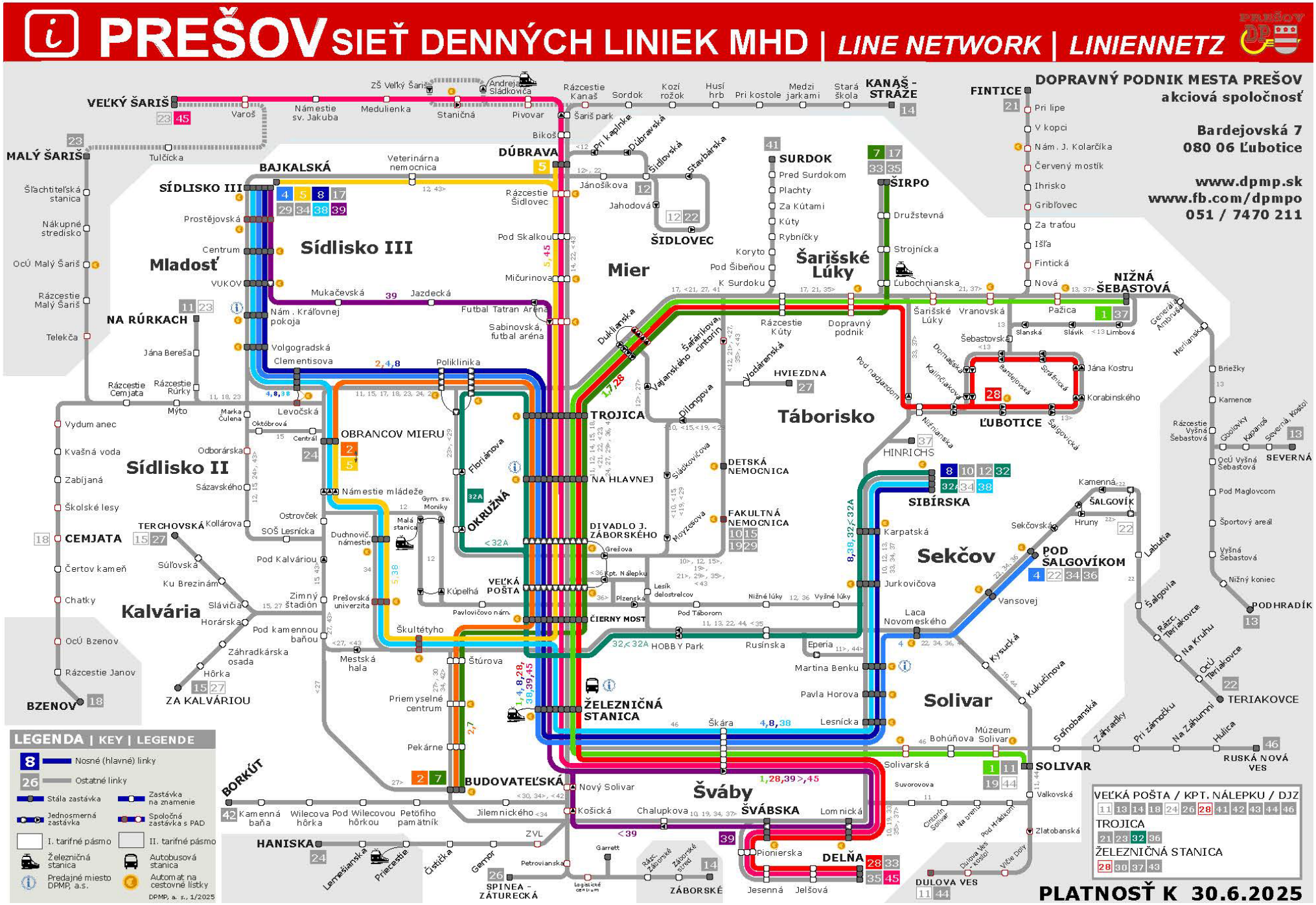
8.2 Sieť denných liniek MHD